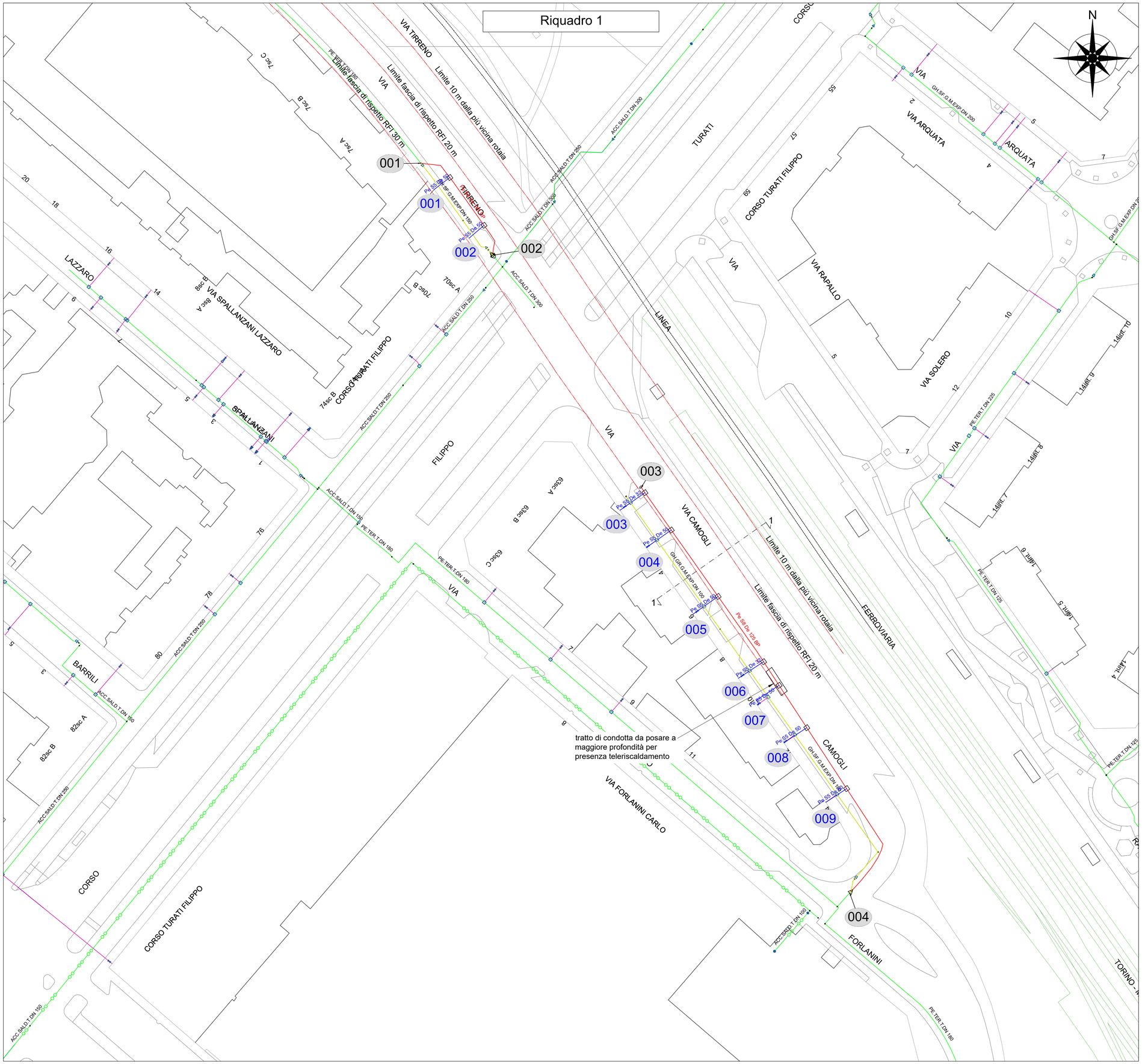

KEY PLAN

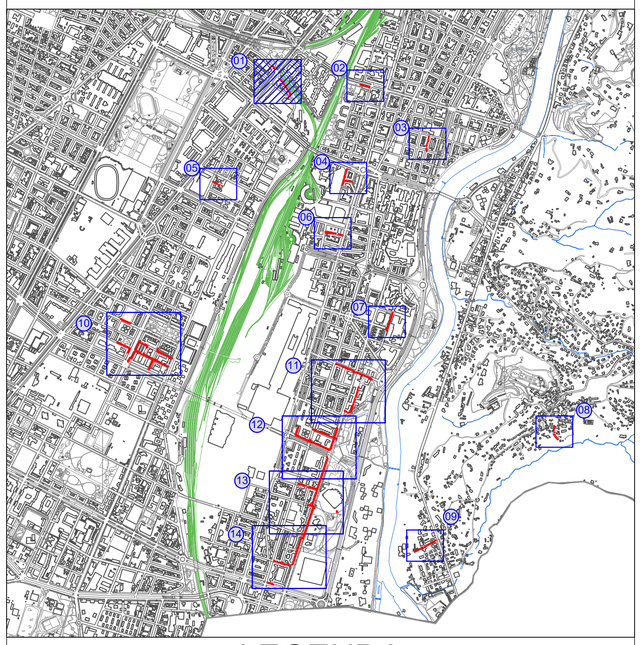

LEGENDA

- Rete in progetto BP
- Tubazione I.D.U. esistente
- Rete da rimuovere
- Tubazione I.D.U. in progetto
- Organo di presa
- (001) Numero I.D.U. in progetto

Riepilogo allacciamenti

n.	Posizione	Tipologico	diametro esistente		diametro di progetto		lunghezza (L) [m]	ΔH[m]	L.privata >12m [m]
			Acc DN	Pe De	Acc DN	Pe De			
001	Via Camogli snc					50	5,50		
002	Via Camogli snc					50	5,50		
003	C.so Turati civ. 63 da via Camogli	3	25	-	-	32	8,50		
004	C.so Turati civ. 63 da via Camogli	3	40	-	-	50	8,50		
005	Via Camogli civ. 6	3	40	-	-	50	8,50		
006	Via Camogli civ. 8	3	25	-	-	32	8,00		
007	Via Camogli civ. 10	3	40	-	-	50	9,00		
008	Via Camogli civ. 12	3	40	-	-	50	7,50		
009	Via Camogli civ. 14	3	40	-	-	50	7,00		

geopavia

Progettista:
Ing. Claudio Gatti
Ordine degli Ingegneri di Pavia
Albo n. 3197

Unità Responsabile della Progettazione
INGEREAL-INGE-PROGRE

Progetto n°:
21-0564-3E-00-001272
WBS: SI.20.I0300.02.1109
Codice elaborato: 25.1 Tavola:

Nome file: AI.25.dwg
Formato: A1 Scala: 1:500

Descrizione:	Rev.	G.	M.	A.	Redatto	Controllato	Approvato
Emissione per progetto esecutivo	00	28	01	26	A. Inglardi	L. Domingo	C. Gatti
Comm.: 2464							

Committente:
Italgas Reti

Comune di Torino (TO) - Vie Varie
PROGETTO ESECUTIVO
SOSTITUZIONE RETE BP (2.745,39 m) - GARA TO1
Intervento n° SI-036213-001272-TSS-TORIN008

Planimetria di localizzazione IDU - Tavola 1

Il presente elaborato è di proprietà aziendale - La società tutelerà i propri diritti a termini di legge.

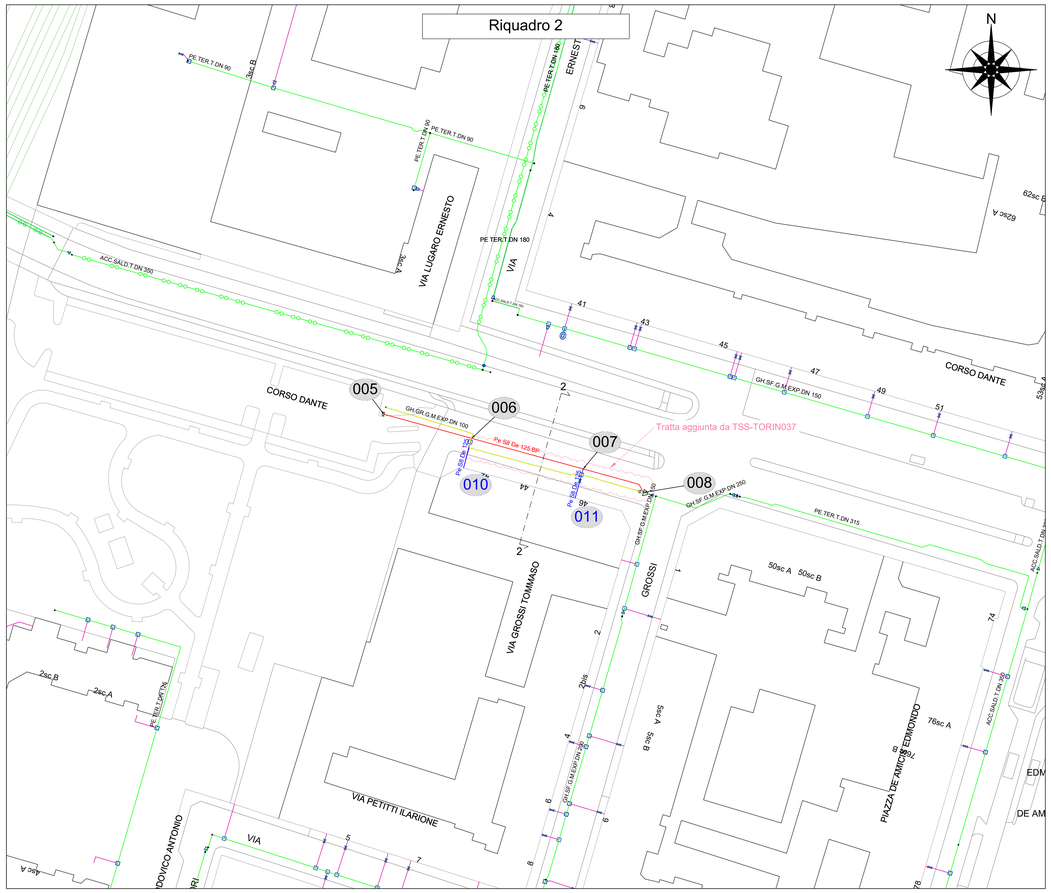

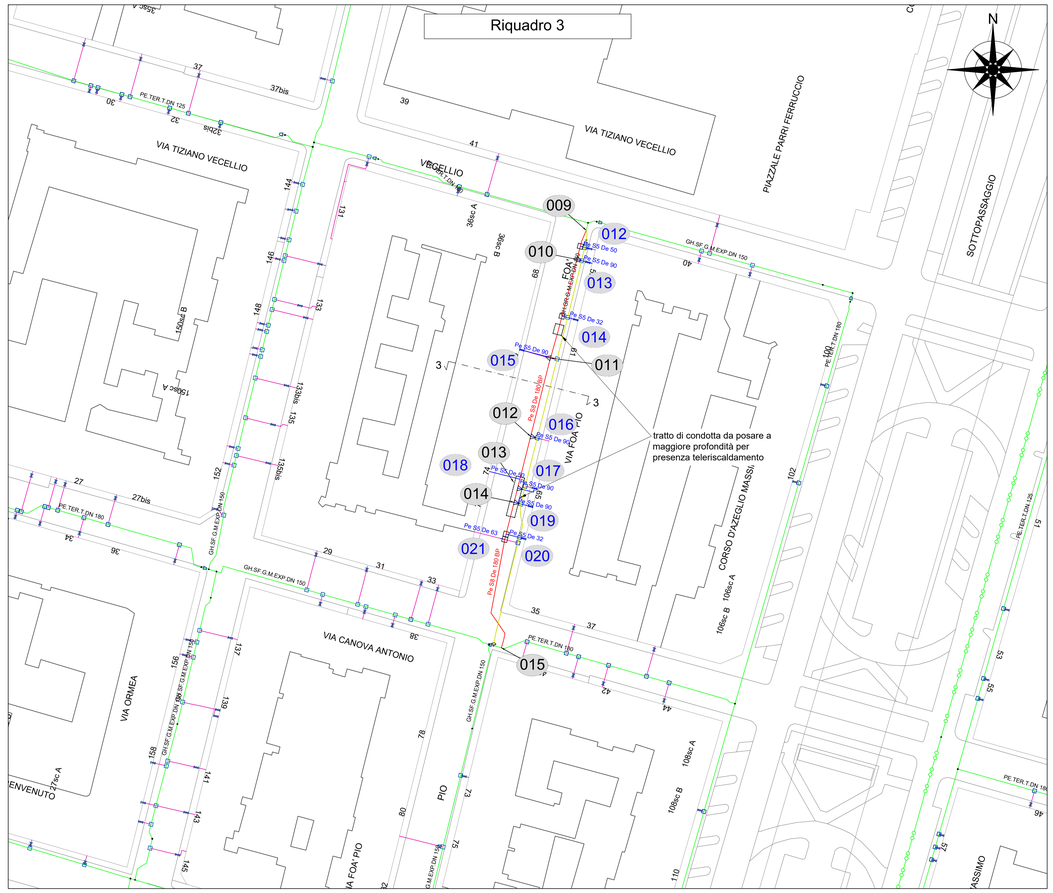

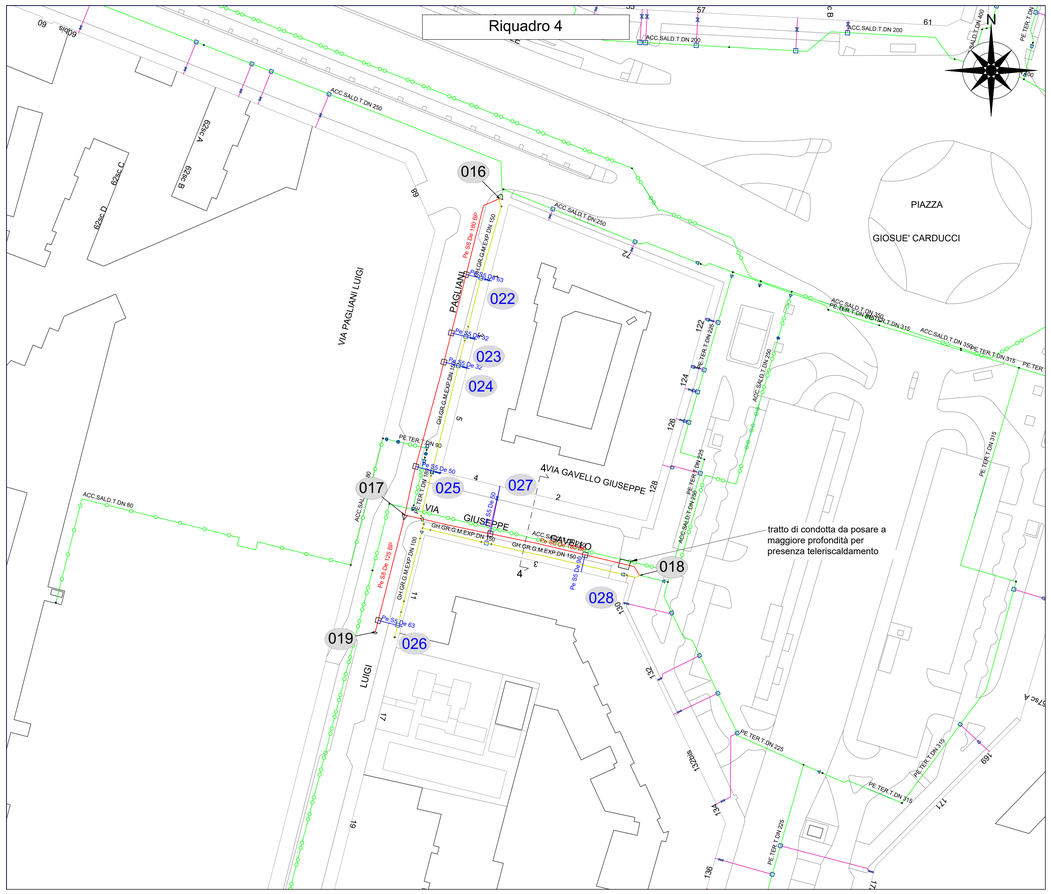

KEY PLAN

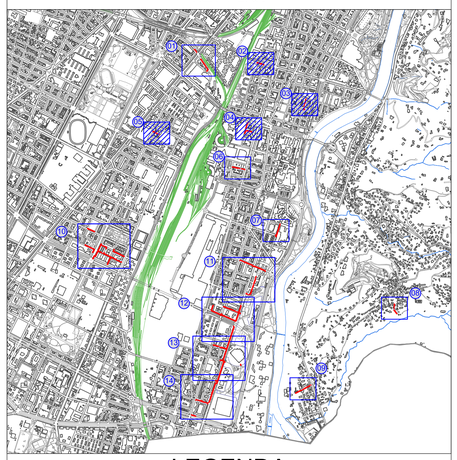

LEGENDA

- Rete in progetto BP
- Tubazione I.D.U. esistente
- Rete da rimuovere
- Tubazione I.D.U. in progetto
- Organo di presa
- 001 Numero I.D.U. in progetto

Riepilogo allacciamenti

n.	Posizione	Tipologico	diametro esistente Acc DN	diametro esistente Pe De	diametro di progetto Acc DN	diametro di progetto Pe De	lunghezza (L) [m]	ΔH[m]	L>m >12m [m]
010	Corso Alighieri Dante civ. 42	3	100	-	-	125	7,00		
011	Corso Alighieri Dante civ. 46	3	100	-	-	125	7,00		
012	Via Foa' Pio snc	1	-	50	-	50	2,00		
013	Via Foa' Pio civ. 59	3	75	-	-	90	3,50		
014	Via Foa' Pio civ. 61	3	25	-	-	32	4,00		
015	Via Foa' Pio civ. 68	4	80	-	-	90	7,50		
016	Via Foa' Pio civ. 63	1	-	90	-	90	2,50		
017	Via Foa' Pio civ. 65	1	-	90	-	90	5,50		
018	Via Foa' Pio civ. 74					50	7,50		
019	Via Foa' Pio civ. 65	3	75	-	-	90	4,50		
020	Via Foa' Pio civ. 65	3	25	-	-	32	4,50		
021	Via Foa' Pio civ. 76	2	-	63	-	63	1,00		
022	Via Pagliani Luigi civ. 1	3	50	-	-	63	6,00		
023	Via Pagliani Luigi civ. 3	3	25	-	-	32	6,00		
024	Via Pagliani Luigi civ. 3	3	32	-	-	32	6,50		
025	Via Pagliani Luigi civ. 5	3	40	-	-	50	6,00		
026	Via Gavello Giuseppe civ. 4	4	40	-	-	50	11,00		
027	Via Gavello Giuseppe civ. 3					90	8,00		
028	Via Pagliani Luigi civ. 11	1	-	63	-	63	5,50		
029	Via Tunisi civ. 45 int. 3	1	-	50	-	50	2,50		
030	Via Tunisi civ. 45 int. 5	3	50	-	-	63	3,00		
031	Via Tunisi civ. 45 int. 6	4	40	-	-	50	2,50		

geopavia

Progettista: Ing. Claudio Gatti, Ordine degli Ingegneri di Pavia, Albo n. 3197

Unità Responsabile della Progettazione: INGEREAL-INGE-PROGRE

Progetto n°: 21-0564-3E-00-001272
WBS: SI.20.I030.02.1109
Codice elaborato: 25.2 Tavola:

Nome file: AI.25.dwg

Formato: A1 Scala: 1:500

Rev.	G.	M.	A.	Redatto	Controllato	Approvato
00	28	01	26	A. Inglardi	L. Domingo	C. Gatti

Descrizione: Emissione per progetto esecutivo

Comm.: 2464

Committente: Italgas Reti

Comune di Torino (TO) - Vie Varie

PROGETTO ESECUTIVO
SOSTITUZIONE RETE BP (2.745,39 m) - GARA TO1
Intervento n° SI-036213-001272-TSS-TORIN008

Planimetria di localizzazione IDU - Tavola 2

Il presente elaborato è di proprietà aziendale - La società tutelerà i propri diritti a termini di legge.

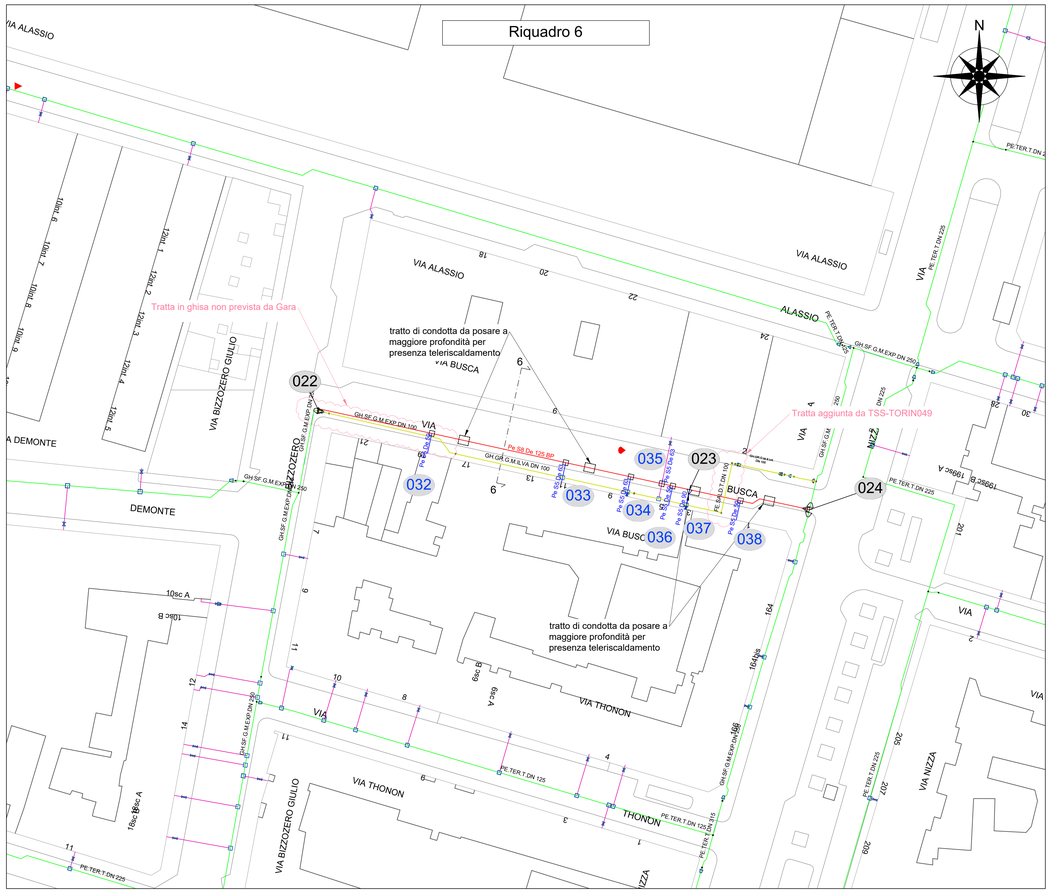

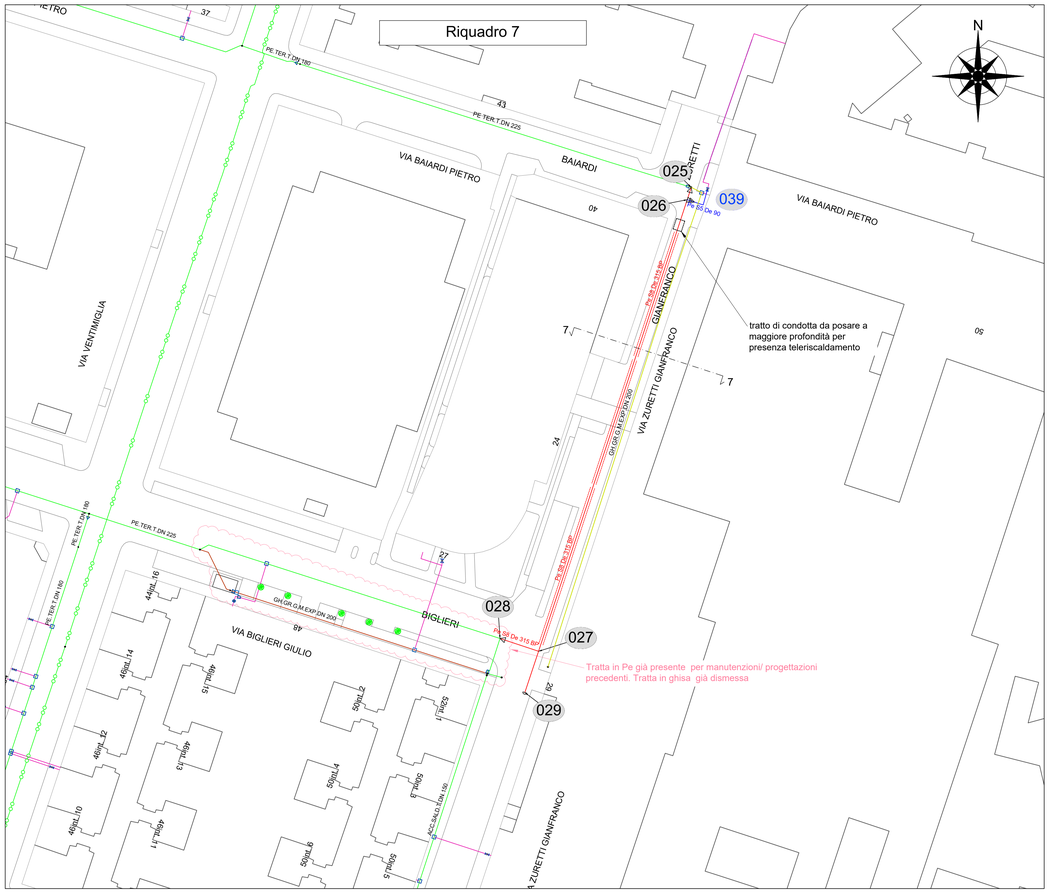

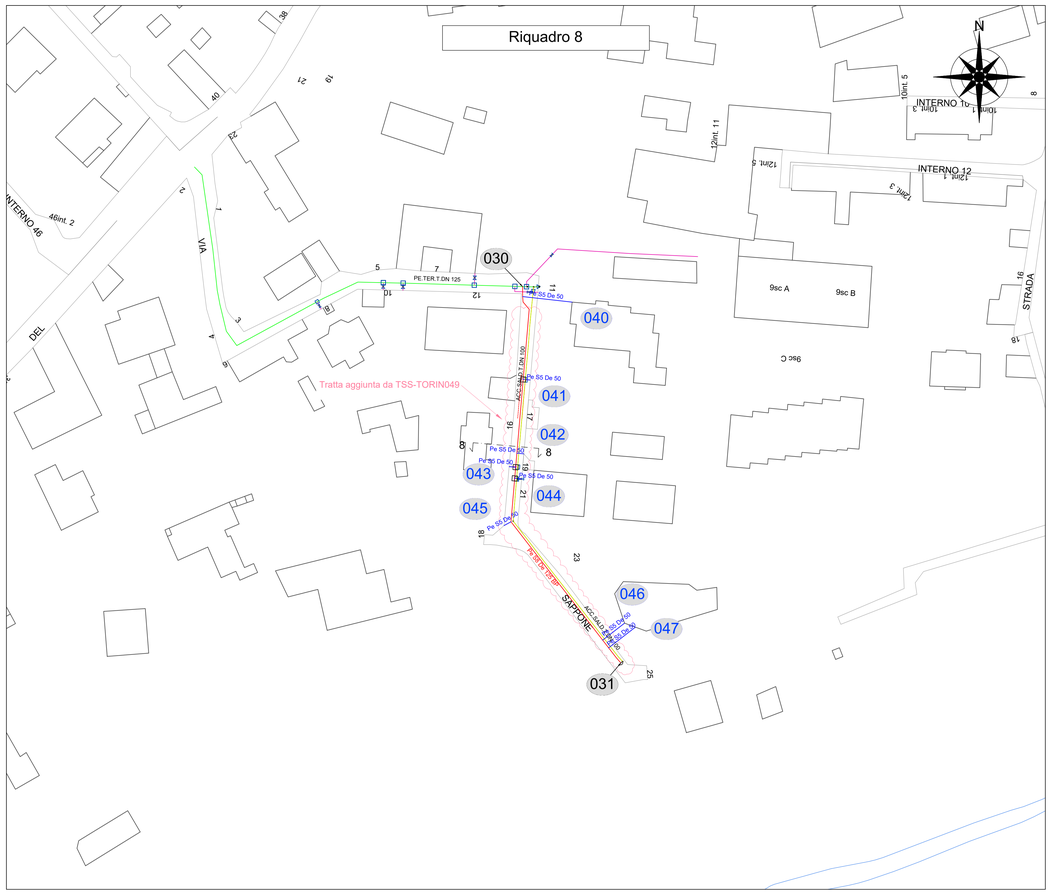

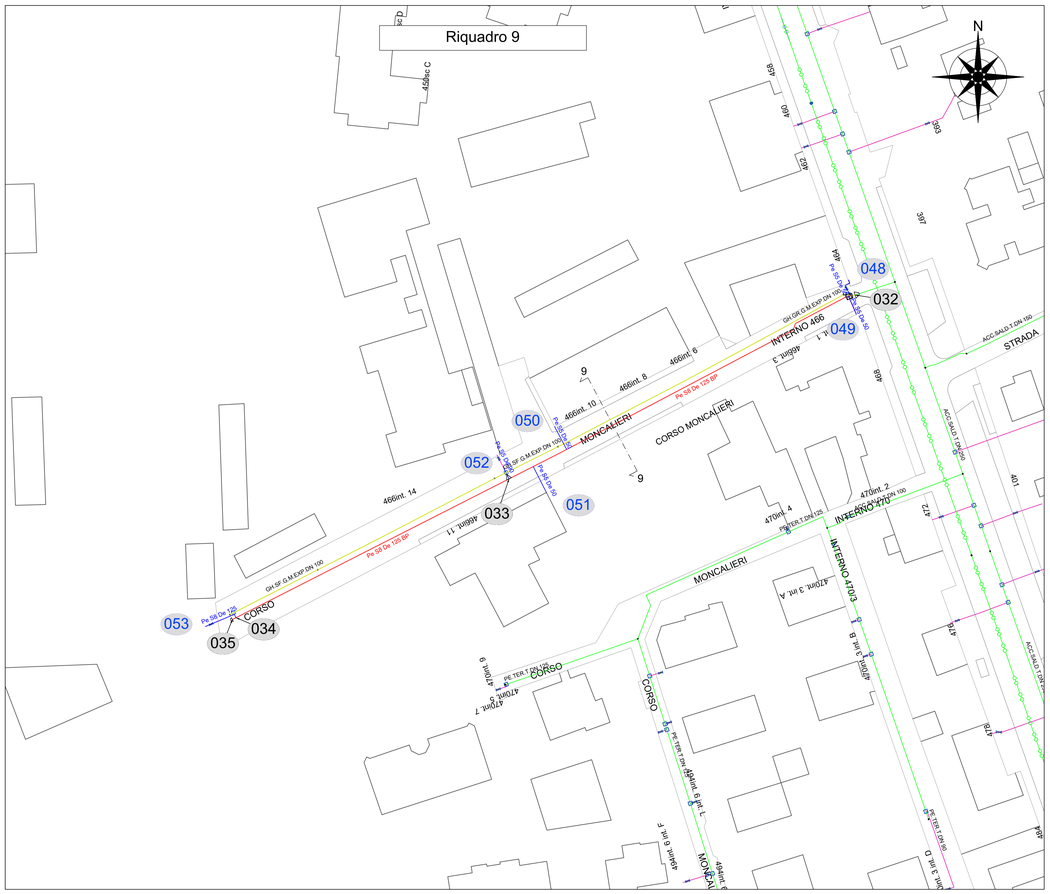

KEY PLAN

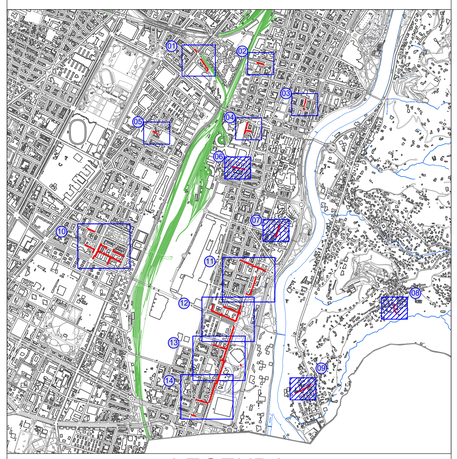

LEGENDA

- Rete in progetto BP
- Tubazione I.D.U. esistente
- Rete da rimuovere
- Tubazione I.D.U. in progetto
- Organo di presa
- 001 Numero I.D.U. in progetto

Riepilogo allacciamenti

n.	Posizione	Tipologico	diametro esistente Acc DN	diametro esistente Pe De	diametro di progetto Acc DN	diametro di progetto Pe De	lunghezza (L) [m]	ΔH[m]	L prriseta >12m [m]
032	Via Busca civ. 19				50	5,00			
033	Via Busca civ. 11	3	50	-	63	4,50			
034	Via Busca civ. 9	3	50	-	63	4,50			
035	Via Busca civ. 6	2	-	63	63	1,00			
036	Via Busca civ. 5				50	4,50			
037	Via Busca civ. 5	3	75	-	90	4,50			
038	Via Busca civ. 1				50	4,50			
039	Via Baiardi Pietro ang. Via Zuretti	1	-	90	90	7,50			
040	Via Sappone civ. 11				50	11,50			
041	Via Sappone civ. 17	5	40	-	50	1,50	2,00		
042	Via Sappone civ. 19				50	1,50			
043	Via Sappone civ. 16	3	40	-	50	2,00			
044	Via Sappone civ. 21	3	40	-	50	2,00			
045	Via Sappone civ. 18				50	1,50			
046	Via Sappone civ. 25				50	7,00			
047	Via Sappone civ. 25				50	7,00			
048	Corso Moncalieri civ. 464	3	40	-	50	5,00			
049	Corso Moncalieri civ. 466 int.1	6	40	-	50	4,50	2,00		
050	Corso Moncalieri civ. 466 int.10				50	6,00			
051	Corso Moncalieri civ. 466 int.11				50	7,00			
052	Corso Moncalieri civ. 466 int.14	1	-	90	-	90	2,50		
053	Corso Moncalieri civ. 466 int.16	3	100	-	-	125	8,00		

geopavia

Progettista:
Ing. Claudio Gatti
Ordine degli Ingegneri di Pavia
Albo n. 3197

Unità Responsabile della Progettazione
INGEREAL-INGE-PROGRE

Progetto n°:
21-0564-3E-00-001272
WBS: SI.20.I030.02.1109
Codice elaborato: 25.3 Tavola:

Nome file: AI.25.dwg
Formato: A1 Scala: 1:500

Rev.	G.	M.	A.	Redatto	Controllato	Approvato
00	28	01	26	A. Inglardi	L. Domingo	C. Gatti

Descrizione: Emissione per progetto esecutivo
Comm.: 2464

Committente:
Italgas Reti

Comune di Torino (TO) - Vie Varie

PROGETTO ESECUTIVO
SOSTITUZIONE RETE BP (2.745,39 m) - GARA TO1
Intervento n° SI-036213-001272-TSS-TORIN008

Planimetria di localizzazione IDU - Tavola 3

Il presente elaborato è di proprietà aziendale - La società tutelerà i propri diritti a termini di legge.

KEY PLAN

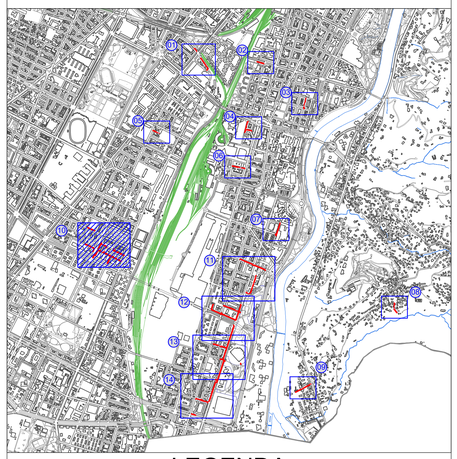

LEGENDA

- Rete in progetto BP
- Tubazione I.D.U. esistente
- Rete da rimuovere
- Tubazione I.D.U. in progetto
- Organo di presa
- 001 Numero I.D.U. in progetto

Riepilogo allacciamenti

n.	Posizione	Tipologico	diametro esistente		diametro di progetto		lunghezza (L) [m]	ΔH[m]	L priseta >12m [m]
			Acc.DN	Pe De	Acc.DN	Pe De			
054	Via Asuncion civ. snc					50	13.00		
055	Via La Loggia civ. 39					50	7.50		
056	Via La Loggia civ. 38/A	4	75	-	-	90	7.50		
057	Via La Loggia civ. 38					50	7.50		
058	Via La Loggia civ. 38	4	80	-	-	90	8.00		
059	Via La Loggia civ. 38					50	7.50		
060	Corso Corsica civ. 7 int. 47	3	50	-	-	63	5.50		
061	Corso Corsica civ. 7 int. 47	3	80	-	-	90	5.50		
062	Corso Corsica civ. 7 int. 9					50	3.50		
063	Corso Corsica civ. 7 int. 49	3	50	-	-	63	5.50		
064	Corso Corsica civ. 7 int. 51					50	5.50		
065	Via Albenga civ. 11 int. 2					50	8.00		
066	Via Albenga civ. 13 da Via Albenga int. 11	3	80	-	-	90	8.00		
067	Via Albenga civ. 11 int. 4					50	8.00		
068	Via Albenga civ. 11 int. 4					90	8.00		
069	Via Albenga civ. 11 int. 4					90	8.00		
070	Via Albenga civ. 11 int. 4					50	8.00		
071	Via Albenga civ. 11 int. 6					50	8.00		
072	Via La Loggia civ. snc					50	11.00		
073	Via La Loggia civ. 51 int. 3	1	-	63	-	63	5.50		
074	Via La Loggia civ. snc					90	11.00		
075	Via La Loggia civ. 19					50	11.00		
076	Via La Loggia civ. 62					50	11.00		
077	Via La Loggia civ. 63	3	80	-	-	90	3.00		
078	Via La Loggia civ. 67	3	80	-	-	90	4.00		
079	Via La Loggia civ. 67					50	4.00		
080	Corso Corsica civ. 19	3	25	-	-	32	17.50		

geopavia

Progettista:
Ing. Claudio Gatti
Ordine degli Ingegneri di Pavia
Albo n. 2197

Unità Responsabile della Progettazione
INGEREAL-INGE-PROGRE

Progetto n°:
21-0564-3E-00-001272
WBS: SI.20.I0300.02.1109
Codice elaborato: 25.4 Tavola:

Nome file: 4t.20.dwg
Formato: A1 Scala: 1:500

Committente:
Italgas Reti

Rev.	G.	M.	A.	Redatto	Controllato	Approvato
00	28	01	26	A. Ingiardi	L. Domingo	C. Gatti

Descrizione: Emissione per progetto esecutivo
Comm.: 2464

Comune di Torino (TO) - Vie Varie
PROGETTO ESECUTIVO
SOSTITUZIONE RETE BP (2.745,39 m) - GARA TO1
Intervento n° SI-036213-001272-TSS-TORIN008
Planimetria di localizzazione IDU - Tavola 4

Il presente elaborato è di proprietà aziendale - La società tutelerà i propri diritti a termini di legge.

KEY PLAN

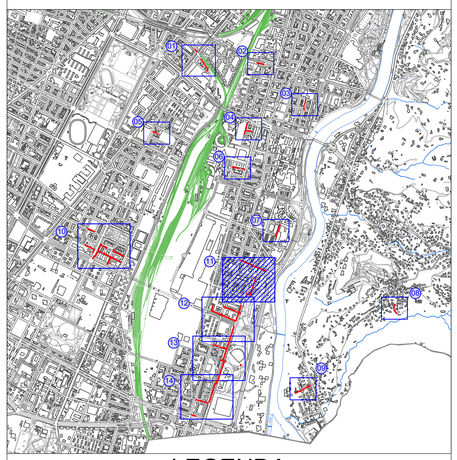

LEGENDA

- Rete in progetto BP
- Tubazione I.D.U. esistente
- Rete da rimuovere
- Tubazione I.D.U. in progetto
- Organo di presa
- 001 Numero I.D.U. in progetto

Riepilogo allacciamenti

n.	Posizione	Tipologico	diametro esistente		diametro di progetto		lunghezza (L) [m]	ΔH[m]	Lpriata >12m [m]
			Acc DN	Pe De	Acc DN	Pe De			
081	Via Garessio civ. 18	3	40	-	-	50	6,50		
082	Via Garessio civ. 23					50	9,00		
083	Via Garessio civ. 18	3	50	-	-	63	6,50		
084	Via Garessio civ. 27	4	80	-	-	90	13,50		
085	Via Garessio civ. 24 int.2 da Via Garessio	3	80	-	-	90	9,00		
086	Via Garessio civ. 29	3	50	-	-	63	13,50		
087	Via Garessio civ. 33 int. 2A					50	9,00		
088	Via Garessio civ. 33 int. 2A					50	9,00		
089	Via Garessio civ. 24 int 5 da Via Garessio	5	-	63	-	63	6,00	2,00	
090	Via Garessio civ. 37	4	75	-	-	90	13,50		
091	Via Garessio civ. 39					50	14,00		
092	Via Garessio civ. 45	4	50	-	-	63	14,00		
093	Via Garessio civ. 47					50	14,00		
094	Via Garessio civ. 48 int. 5	4	50	-	-	63	3,00		
095	Via Millefonti civ. 39 int. 4	4	50	-	-	63	1,50		
096	Via Millefonti civ. 43 da Via Millefonti civ. 39	2	-	63	-	63	1,00		
097	Largo Millefonti civ. 35	3	50	-	-	63	3,50		

geopavia

Progetto n°:
21-0564-3E-00-001272
WBS: S.20.0300.02.1109
Codice elaborato: 25.5 Tavola:

Nome file: AI.25.dwg
Formato: A1 Scala: 1:500

Committente:
Italgas Reti

Progettista:
Ing. Claudio Gatti
Ordine degli Ingegneri di Pavia
Albo n. 3197

Unità Responsabile della Progettazione
INGEREAL-INGE-PROGRE

Descrizione	Rev.	G.	M.	A.	Redatto	Controllato	Approvato
Emissione per progetto esecutivo	00	28	01	26	A. Inglardi	L. Domingo	C. Gatti
Comm.: 2464							

Comune di Torino (TO) - Vie Varie

PROGETTO ESECUTIVO
SOSTITUZIONE RETE BP (2.745,39 m) - GARA TO1
Intervento n° SI-036213-001272-TSS-TORIN008

Planimetria di localizzazione IDU - Tavola 5

Il presente elaborato è di proprietà aziendale - La società tutelerà i propri diritti a termini di legge.

Riquadro 12

Tratta rimossa per ottimizzazione

Tratta aggiunta per ottimizzazione

Tratta aggiunta da TSS-TORIN049

tratto di condotta da posare a maggiore profondità per presenza teleriscaldamento

coll. equipotenziale esistente

Tratta eliminata da TSS-TORIN049 prevista sola dismissione

VIA NIZZA — PIAZZA FILZI FABIO — PIAZZA FABIO FILZI — VIA GENOVA — VIA GIAGLIONE — VIA VENTIMIGLIA — PISTA DI PATTINAGGIO — CORSO CADUTI SUL LAVORO — SOTTOPASSAGGIO CADUTI SUL LAVORO — VIA VALENZA

KEY PLAN

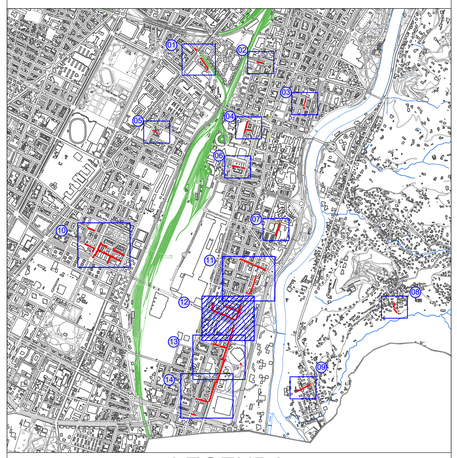

LEGENDA

- Rete in progetto BP
- Tubazione I.D.U. esistente
- Rete da rimuovere
- Tubazione I.D.U. in progetto
- Organo di presa
- 001 Numero I.D.U. in progetto

Riepilogo allacciamenti

n.	Posizione	Tipologico	diametro esistente		diametro di progetto		lunghezza (L) [m]	ΔH[m]	Lpriata >12m [m]
			Acc DN	Pe De	Acc DN	Pe De			
098	Corso Caduti sul Lavoro civ. snc					50	7,00		
099	Via Genova civ. 127 da Via Giaglione	3	80	-	-	90	6,00		
100	Via Giaglione civ. 1	3	65	-	-	63	8,50		
101	Via Giaglione civ. 7	3	75	-	-	90	4,00		
102	Via Giaglione civ. 7					90	4,00		
103	Via Ventimiglia civ. 112	3	50	-	-	63	8,50		
104	Via Ventimiglia civ. 128	3	50	-	-	63	6,50		
105	Via Ventimiglia civ. 128					50	20,00		

geopavia

Progettista: Ing. Claudio Gatti, Ordine degli Ingegneri di Pavia Albo n. 3197

Unità Responsabile della Progettazione: INGEREAL-INGE-PROGRE

Progetto n°: 21-0564-3E-00-001272

WBS: SI.20.I0300.02.1109

Codice elaborato: 25.6 Tavola:

Nome file: AI.25.dwg

Formato: A1 Scala: 1:500

Commitente: Italgas Reti

Descrizione	Rev.	G.	M.	A.	Redatto	Controllato	Approvato
Emissione per progetto esecutivo	00	28	01	26	A. Inglardi	L. Domingo	C. Gatti
Comm.: 2464							

Comune di Torino (TO) - Vie Varie

PROGETTO ESECUTIVO

SOSTITUZIONE RETE BP (2.745,39 m) - GARA TO1

Intervento n° SI-036213-001272-TSS-TORIN008

Planimetria di localizzazione IDU - Tavola 6

Il presente elaborato è di proprietà aziendale - La società tutelerà i propri diritti a termini di legge.

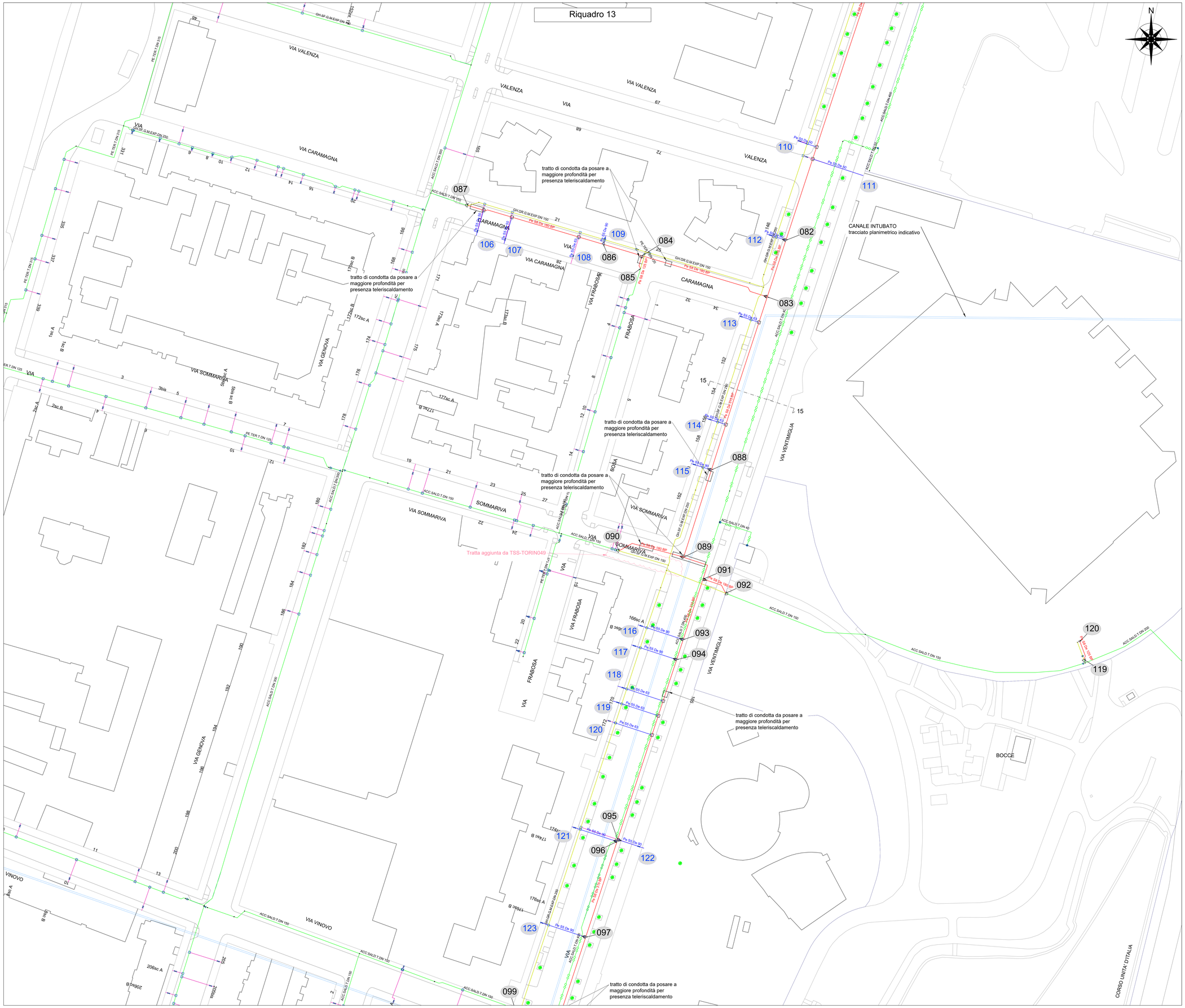

KEY PLAN

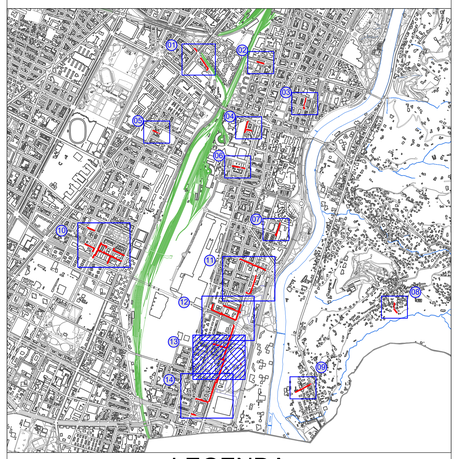

LEGENDA

- Rete in progetto BP
- Tubazione I.D.U. esistente
- Rete da rimuovere
- Tubazione I.D.U. in progetto
- Organo di presa
- 001 Numero I.D.U. in progetto

Riepilogo allacciamenti

n.	Posizione	Tipologico	diametro esistente Acc.DN	diametro esistente Pe De	diametro di progetto Acc.DN	diametro di progetto Pe De	lunghezza (L) [m]	ΔH[m]	Lpriata >12m [m]
106	Via Genova civ.171 da Via Caramagna	4	40	-	-	50	11,00		
107	Via Caramagna civ.26	4	40	-	-	50	11,50		
108	Via Caramagna civ.21	2	-	63	-	63	1,00		
109	Via Caramagna civ.21	3	75	-	-	90	3,50		
110	Via Valenza civ.71 da Via Ventimiglia	3	40	-	-	50	8,00		
111	Via Ventimiglia civ.145	6	40	-	-	50	21,50	2,00	
112	Via Ventimiglia civ.146	3	80	-	-	90	8,00		
113	Via Caramagna civ.34 Via Ventimiglia	3	50	-	-	63	8,00		
114	Via Ventimiglia civ.156	3	50	-	-	63	8,50		
115	Via Ventimiglia civ.160	3	75	-	-	90	8,50		
116	Via Ventimiglia civ.166	3	75	-	-	90	19,50		
117	Via Ventimiglia civ.166	3	75	-	-	90	19,50		
118	Via Ventimiglia civ.168	3	50	-	-	63	19,50		
119	Via Ventimiglia civ.170	3	50	-	-	63	19,50		
120	Via Ventimiglia civ.172	1	-	63	-	63	16,50		
121	Via Ventimiglia civ.174	3	80	-	-	90	19,50		
122	Via Ventimiglia civ.165 alt.civ.174	4	80	-	-	90	11,50		
123	Via Ventimiglia civ.176	3	80	-	-	90	19,50		

geopavia

Progettista:
Ing. Claudio Gatti
Ordine degli Ingegneri di Pavia
Albo n. 3197

Unità Responsabile della Progettazione
INGEREAL-INGE-PROGRE

Progetto n.°:
21-0564-3E-00-001272
WBS: SI.20.I0300.02.1109
Codice elaborato: 25.7 Tavola:

Nome file: AI.25.dwg
Formato: A1 Scala: 1:500

Descrizione	Rev.	G.	M.	A.	Redatto	Controllato	Approvato
Emissione per progetto esecutivo	00	28	01	26	A. Inglardi	L. Domingo	C. Gatti
Comm.: 2464							

Committente:
Italgas Reti

Comune di Torino (TO) - Vie Varie
PROGETTO ESECUTIVO
SOSTITUZIONE RETE BP (2.745,39 m) - GARA TO1
Intervento n° SI-036213-001272-TSS-TORIN008

Planimetria di localizzazione IDU - Tavola 7

Il presente elaborato è di proprietà aziendale - La società tutelerà i propri diritti a termini di legge.

KEY PLAN

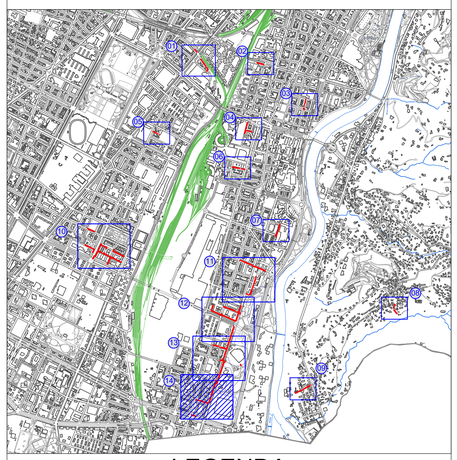

LEGENDA

- Rete in progetto BP
- Tubazione I.D.U. esistente
- Rete da rimuovere
- Tubazione I.D.U. in progetto
- Organo di presa
- 001 Numero I.D.U. in progetto

Riepilogo allacciamenti

n.	Posizione	Tipologico	diametro esistente		diametro di progetto		lunghezza (L) [m]	ΔH[m]	Lpriseta >12m [m]
			Acc DN	Pe De	Acc DN	Pe De			
124	Via Ventimiglia civ. 199	4	50	-	-	63	22,50		
125	Via Ventimiglia civ. 200	3	80	-	-	90	8,00		
126	Via Ventimiglia civ. 200	3	150	-	-	180	8,00		
127	Via Ventimiglia civ. 202	3	80	-	-	90	8,00		
128	Via Ventimiglia civ. 204	3	80	-	-	90	8,00		
129	Via Testona civ. 31					50	6,00		
130	Via Testona civ. 23	4	75	-	-	90	6,00		
131	Via Testona civ. 21	4	80	-	-	90	6,00		
132	Via Genova civ. 231 da Via Testona	1	-	63	-	63	9,00		
133	Via Genova civ. 231 da Via Testona	3	25	-	-	32	9,00		
134	Via Genova civ. 231 da Via Testona	3	50	-	-	63	9,00		
135	Via Testona civ. 26	3	50	-	-	63	5,50		
136	Via Testona civ. 26	3	75	-	-	90	5,50		
137	Via Testona civ. 28	3	75	-	-	90	5,50		
138	Via Testona civ. 28	3	50	-	-	63	5,50		
139	Via Testona civ. 30	3	75	-	-	90	5,50		
140	Via Ventimiglia civ. 208 da Via Testona	3	80	-	-	90	5,50		
141	Corso Maroncelli Pietro civ. 12	3	80	-	-	90	6,00		
142	Corso Maroncelli Pietro civ. 12					50	6,00		
143	Corso Maroncelli Pietro civ. 10	1	-	63	-	63	2,00		

geopavia

Progettista:
Ing. Claudio Gatti
Ordine degli Ingegneri di Pavia
Albo n. 3197

Unità Responsabile della Progettazione
INGEREAL-INGE-PROGRE

Progetto n°:
21-0564-3E-00-001272
WBS: SI.20.I0300.02.1109
Codice elaborato: 25.8 Tavola:

Nome file: AI.25.dwg
Formato: A1 Scala: 1:500

Descrizione:
Emissione per progetto esecutivo
Comm.: 2464

Rev.	G.	M.	A.	Redatto	Controllato	Approvato
00	28	01	26	A. Inglardi	L. Domingo	C. Gatti

Committente:
Italgas Reti

Comune di Torino (TO) - Vie Varie
PROGETTO ESECUTIVO
SOSTITUZIONE RETE BP (2.745,39 m) - GARA TO1
Intervento n° SI4036213-001272-TSS-TORIN008

Planimetria di localizzazione IDU - Tavola 8

Il presente elaborato è di proprietà aziendale - La società tutelerà i propri diritti a termini di legge.