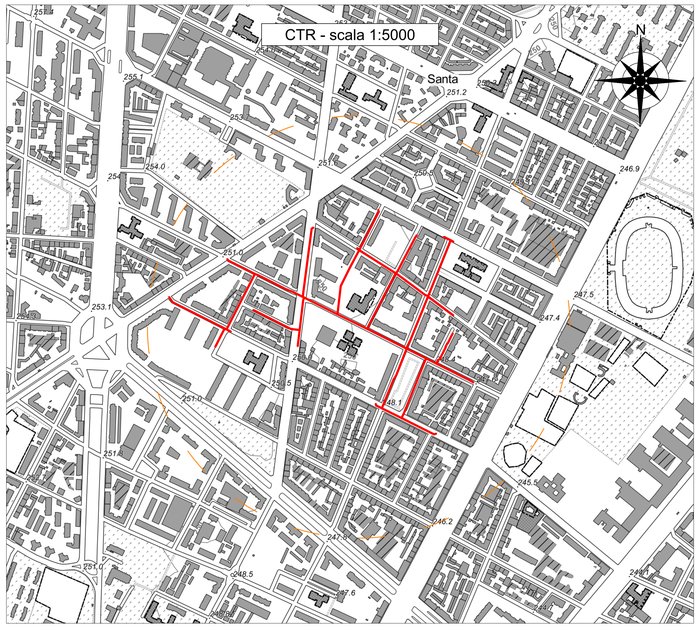

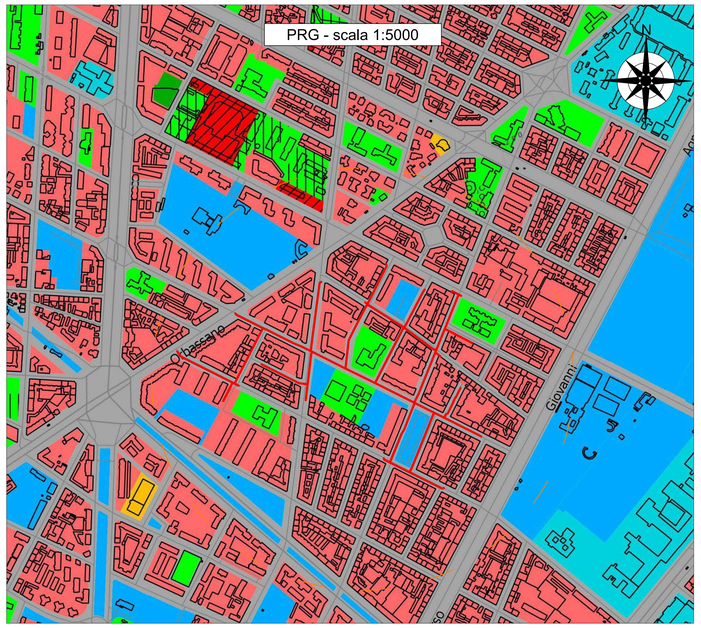

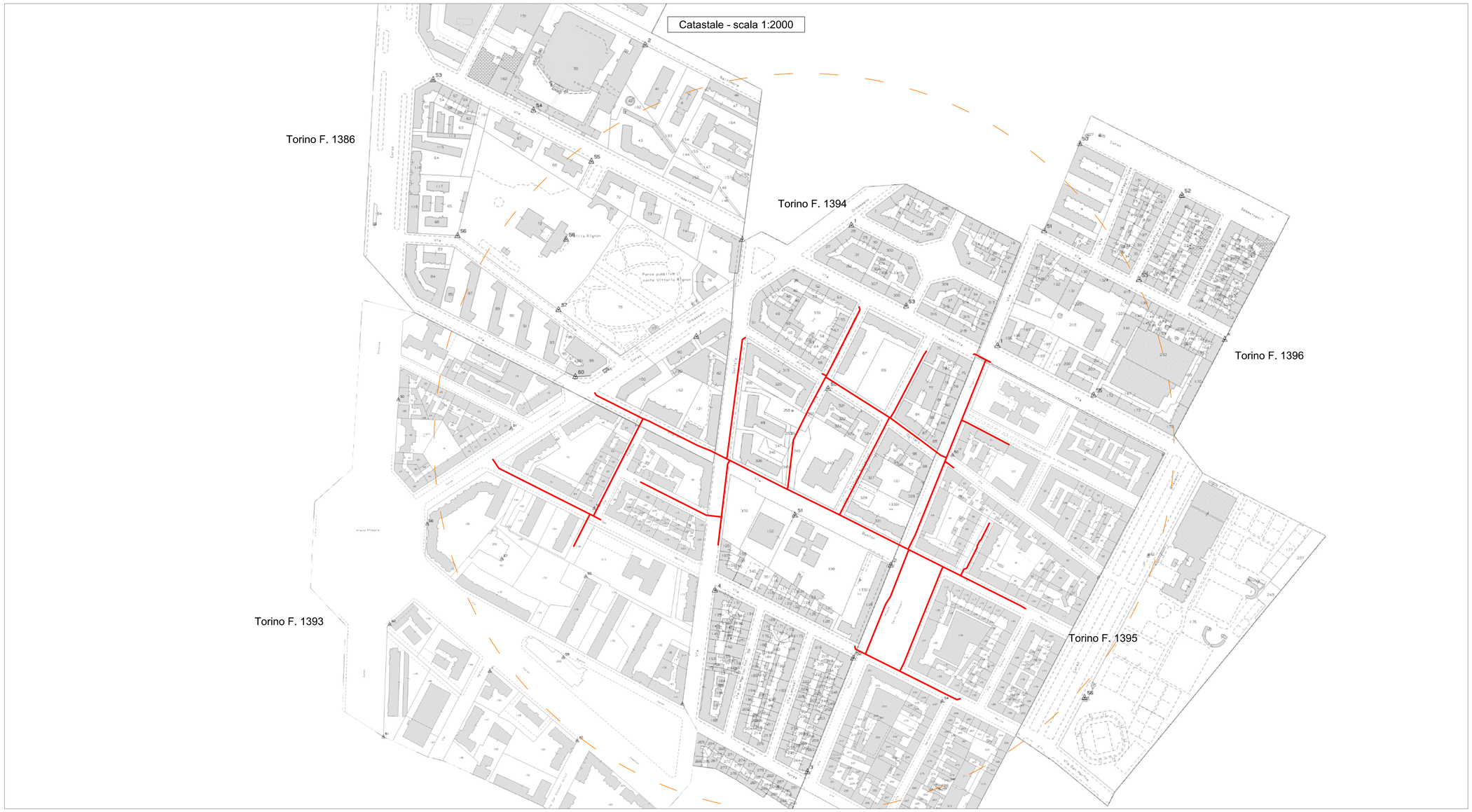

KEY PLAN

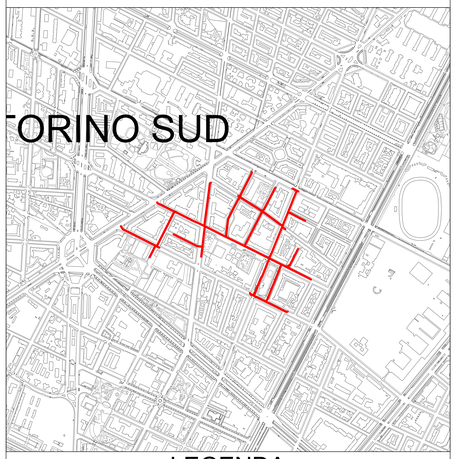

LEGENDA

- Rete in progetto
- Confini comunali
- Area di interesse

DESTINAZIONI D'USO PREVALENTI E COMPROMISSIONE TERRITORIALE

RESIDENZIALE
PRODUTTIVO
TERZIARIO
POLIFUNZIONALE
TURISTICO-RICETTIVO
AMBITI DI VALORE STORICO/AMBIENTALE
CONSOLIDATO E/O COMPLETAMENTO
NUOVO IMPIANTO
TRASFORMAZIONE
NON SPECIFICATO
AGRO-FORESTALE
INDIFFERENZIATO
PREGIO AMBIENTALE
VINCOLATO

ATTREZZATURE PUBBLICHE E DI USO PUBBLICO

Interesse comunale
AMBITI DI VALORE STORICO/AMBIENTALE
ALLA PERSONA E ALLE ATTIVITA'
VERDE / SPORT / PARCHEGGI
INFRASTRUTTURE / IMPIANTI
INDIFFERENZIATE
AMBITI A CONNOTAZIONE NATURALE
Interesse sovracomunale

TEMATISMI DI RIFERIMENTO

Limiti provinciali
Limiti comunali
Aree edificate
Fiumi e laghi
Viabilità stradale
Autostrade e superstrade
Statali
Provinciali
Comunali ed altre strade
Viabilità ferroviaria
Linee esistenti

LEARDI

Progettista:
Alessandro Leardi
Ordine degli Ingegneri di Alessandria
matricola 2101
Firma

ORDINE INGEGNERI PROV. ALESSANDRIA
SETTORI CIVILE AMB. INDUSTRIALE
ALESSANDRO LEARDI
INGEGNERE
N. 2101

Unità Responsabile della Progettazione
INGEREAL-INGE-PROGRE

Progetto n°:
22-0320-3E-00-001272
WBS:
SI.20.I0300.02.1109
ALLEGATO n°: 2
Nome File: m2.dwg
Formato: A0
Scala 1 : -

Descrizione
Descrizione
Emissione per commenti

Rev.	G.	M.	A.	Redatto	Controllato	Approvato
0	04	11	22	A.Saronni	L.Cartasegna	A.Leardi

Comm. : 2464

Committente
Italgas Reti

Comune di
TORINO (TO)
Vie Varie
Progetto Esecutivo
SOSTITUZIONE RETE IN BP (L=2504,78 m) GARA ATEM TO1
Intervento n° SI-036213-001272-TSS-TORIN036
Cartografia

Il presente elaborato è di proprietà aziendale - La società tutelerà i propri diritti a termini di legge.